Scheda 7.1

La mappa del progetto: il campo come sistema complesso

Una forma architettonica nasce da un campo di relazioni, non da un oggetto isolato. La mappa progettuale è il luogo in cui queste relazioni prendono forma: flussi, intensità, gerarchie, nodi, soglie. Ogni elemento si definisce nella rete che lo connette agli altri. Costruire un progetto significa prima costruire un campo strutturale: un sistema interdipendente in cui tutto è in relazione.

A.

Cedric Price, *Fun Palace* (1961)

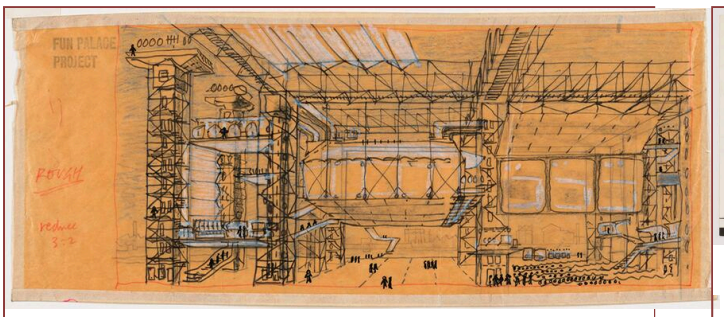

A.1

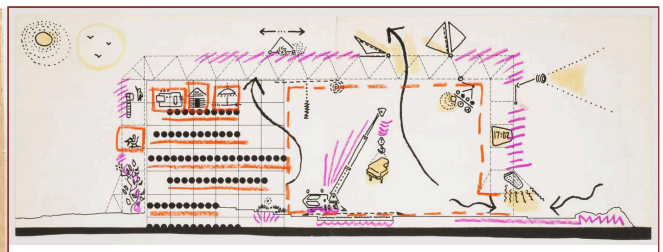

A.2

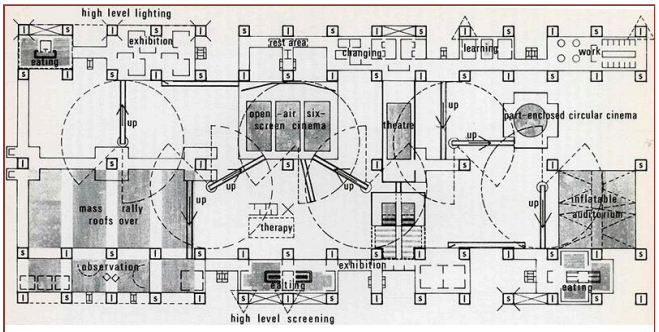

A.3

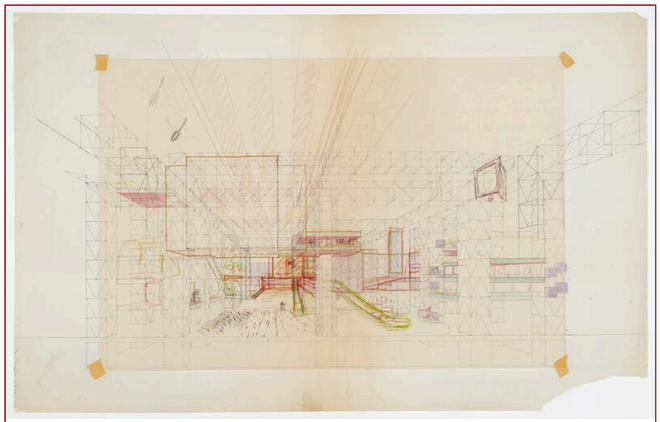

A.4

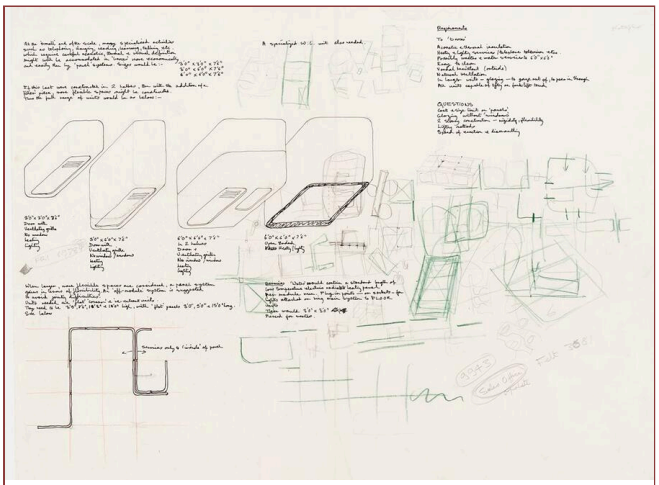

A.5

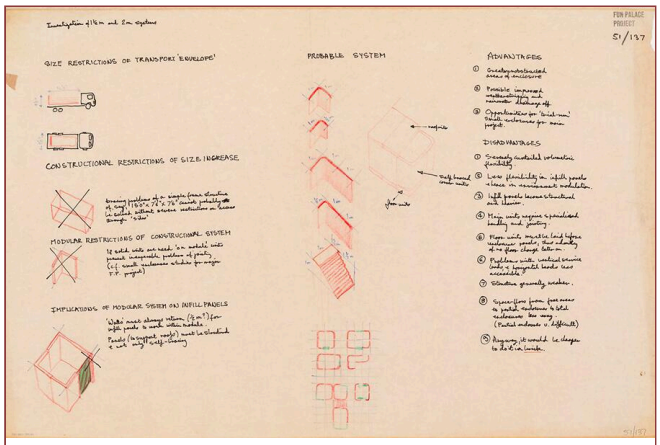

A.6



A.7

Il progetto come campo variabile: una rete di forze, flussi e nodi prima ancora che un edificio.

Il *Fun Palace* non è un'architettura in senso tradizionale, ma una mappa operativa. Cedric Price trasforma il progetto in un sistema di relazioni: una griglia aperta d'acciaio, gru a ponte, moduli mobili (pavimenti, pareti, scale, attrezzature) che si riconfigurano nel tempo. La forma non viene fissata: emerge come comportamento del campo quando persone, tecnologie e attività interagiscono. È la logica che la scheda sinottica della Lezione 7 rende visibile: prima della figura sta il campo complesso e governabile delle dipendenze, delle intensità e dei flussi.

La collaborazione con Gordon Pask introduce la cibernetica: il progetto è concepito come sistema adattivo, capace di "apprendere" dagli usi e di variare in risposta ai desideri mutevoli degli utenti. Anche gli strumenti di rappresentazione riflettono questa impostazione: diagrammi PERT, schemi funzionali, reti decisionali. Le linee non disegnano muri: tracciano vettori, nodi, feedback, cioè le condizioni di funzionamento del campo. L'utente non è spettatore, ma co–autore: manipola lo spazio, programma eventi, riconfigura assetti. Per Price questa è "non–architettura": non un oggetto da contemplare, ma un generatore di possibilità.

Nel quadro della Lezione 7, il *Fun Palace* è esemplare perché sposta l'attenzione dalla forma finita alla struttura relazionale che rende la forma possibile, trasformabile, coerente pur nel cambiamento. La "didascalia" del progetto non è un prospetto o una pianta, ma il **diagramma del sistema**: ciò che consente di leggere componenti e variabili, di governarne le interdipendenze e, soprattutto, di far sì che il progetto resti aperto senza perdere identità.

B.

OMA / Rem Koolhaas, *Project on the City – Atlanta*

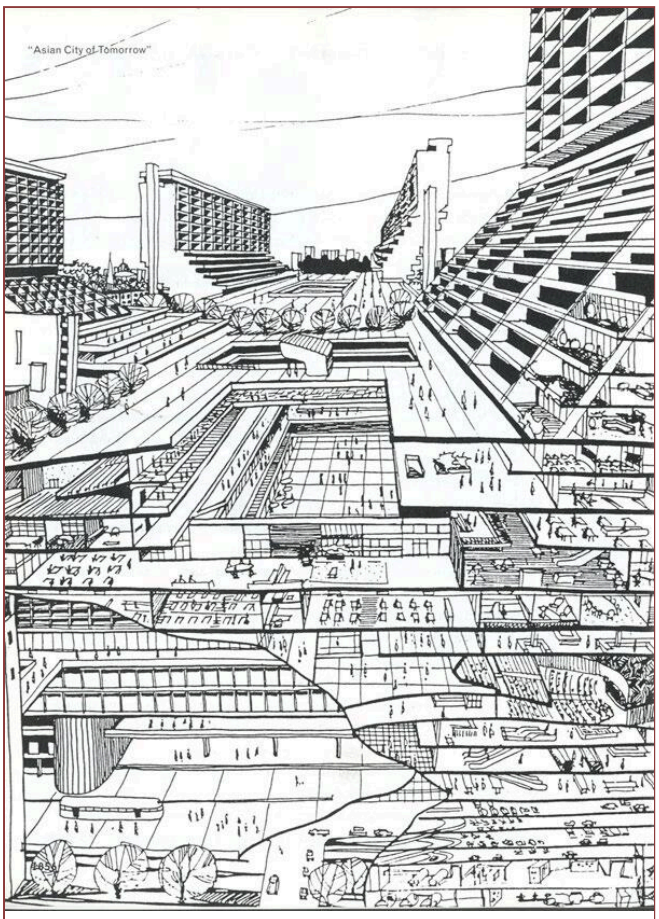

B.1



B.2



B.3



B.4

Una metropoli letta come rete: densità, infrastrutture, flussi e polarità resi visibili in un unico campo.

Direzioni fluide, campi vettoriali, traiettorie che orientano il corpo

Ad Atlanta OMA abbandona la rappresentazione oggettuale della città per trattarla come sistema di forze. I diagrammi non disegnano edifici ma vettori: autostrade, rampe, parcheggi, linee di scambio, corridoi commerciali, flussi di persone e capitali. La città emerge come **centerless city**, priva di un nucleo dominante; al suo posto, quasi-centri prodotti da infrastrutture e da complessi immobiliari autosufficienti. La forma urbana non coincide con il perimetro costruito: è un campo di relazioni che si ridistribuisce dove si addensano accessibilità, consumo, comunicazione.

La cartografia diagrammatica diventa uno strumento di indagine e di decisione: stratifica dati, rende confrontabili fenomeni eterogenei, visualizza gerarchie e dipendenze (tempi di percorrenza, raggi d'influenza, isocrone, colli di bottiglia). In questo linguaggio asciutto, "Bigness" non è un'icona ma un operatore che deforma reti, protocolli e flussi, generando nuove polarità e nuove esclusioni. L'urbanistica è letta come competizione tra infrastrutture e spazio pubblico: ciò che dà ordine non è la figura del lotto, ma il regime di accesso.

Per la scheda sinottica di Lezione 7, Atlanta è paradigmatica: mostra che prima della forma occorre costruire la **mappa relazionale** – **componenti** (luce, vuoto, proporzione nel progetto; qui: reti, nodi, densità) e **variabili** (dimensione, posizione, profondità; qui: intensità dei flussi, velocità, connettività). Progettare non significa aggiungere oggetti ma governare un campo, rendendo visibile e manipolabile ciò che è invisibile a occhio nudo. I diagrammi di OMA insegnano a leggere la città come **organismo dinamico**, dove la coerenza non è un'immagine stabile, ma una **logica di comportamenti** che guida le scelte architettoniche.

C.

SANAA, *Rolex Learning Center* (2004–2010)

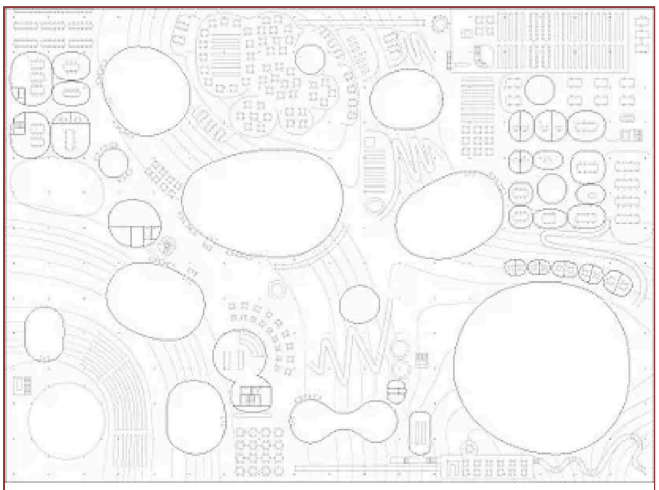

C.1

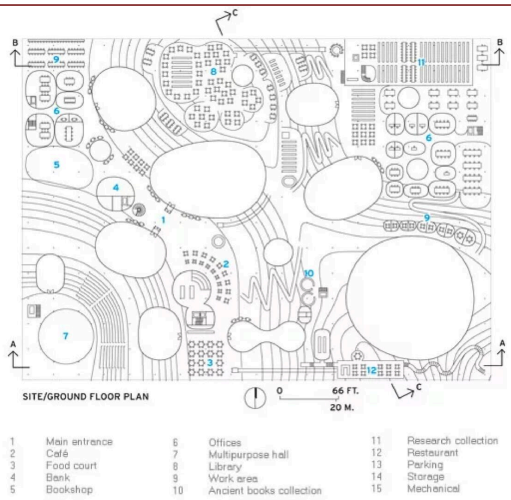

C.2

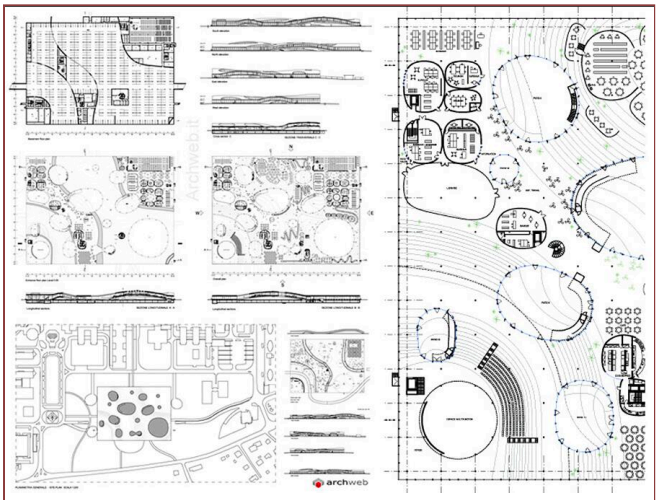

C.3

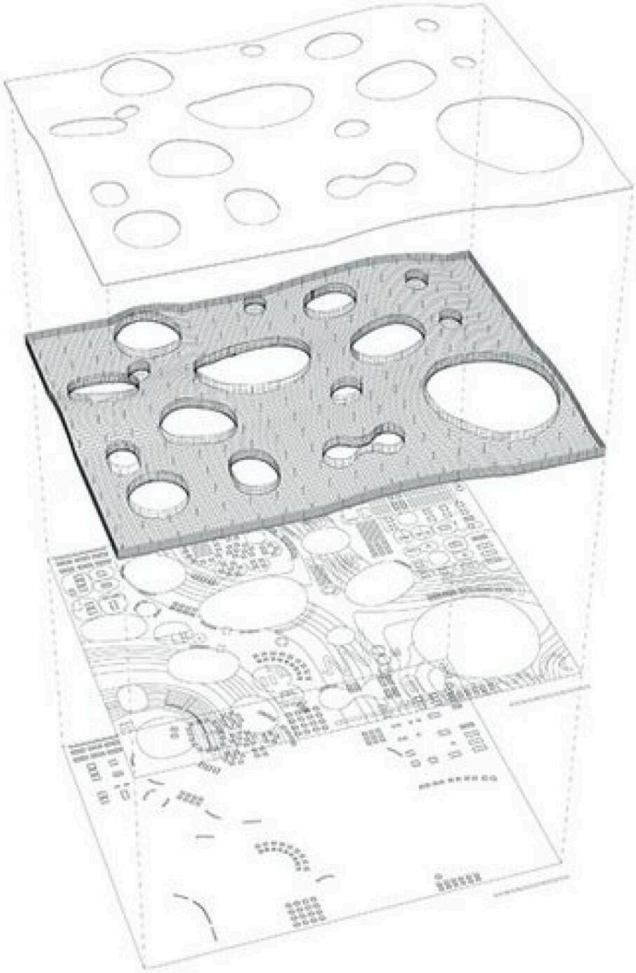

C.4

C.5

C.6



C.7

Non una pianta, ma una mappa di pendenze, flussi, porosità e continuità percettive.

I diagrammi del *Rolex Learning Center* mostrano l'edificio come **paesaggio relazionale**: un unico piano pubblico modellato da lievi pendenze che generano colline e avvallamenti, orientano i flussi e definiscono zone senza ricorrere a pareti. Le aperture circolari (patìi) attraversano il campo portando luce e aria, mettendo in continuità interno ed esterno; la porosità visiva consente di percepire simultaneamente attività diverse, favorendo orientamento e interazione.

Qui la forma non nasce da un volume, ma da una **mappa sinottica** che intreccia componenti (luce, vuoto, proporzione) e variabili (dimensione, posizione, profondità) in un sistema continuo. Le pendenze misurano distanze e tempi di percorrenza; i patìi agiscono come nodi di intensità; le trasparenze stabiliscono connessioni a raggio lungo. L'edificio funziona come campo governabile: cambiano densità, quiete, visibilità, ma la coerenza resta, garantita da una topografia artificiale regolare e da una geometria minima.

Per la Lezione 7, il progetto di SANAA è esemplare: la rappresentazione non ordina "stanze", ma relazioni. La sinossi grafica rende operativi fenomeni

altrimenti invisibili (gradiente di pendenza, traiettorie preferenziali, coni di luce), trasformandoli in regole di comportamento spaziale da cui la forma emerge con naturalezza. È la mappa come strumento critico: prima dell'oggetto, il campo.